CenovaMapa.cz

REPORT

Odhad tržní ceny nemovitosti

Porovnávání kupních cen z listin katastru nemovitostí s aktuálními daty v rámci celé ČR.

REPORT

CenovaMapa.cz

Octopus Pro

www.cenovamapa.cz

DOMY
NA PRODEJ

Informace o nemovitosti,
pro kterou je zobrazena tržní cena

Dotazovaná **nemovitost:**

Kategorie:	**Rodinný dům**
Poskytnutí:	**Na prodej**
Podlahová plocha:	**181 m²**

Filtry výběru:

Konstr. stavby:	-	Plocha (m²):	-
Stáří domu:	**10 let a více**	Počet podlaží:	**2**
		Stav domu:	-
Počet jednotek:	-		

Dotazovaná **lokalita / adresa:**

Č.p. / č.o.:	**191/8**
Ulice:	**Husitská**
Část obce:	**Krupka**
Obec:	**Krupka**
Okres:	**Teplice**
KÚ:	**Krupka (675261)**
GPS:	**Lat: 50.683451**
	Lon: 13.857403

Mapa lokalizace nemovitosti:

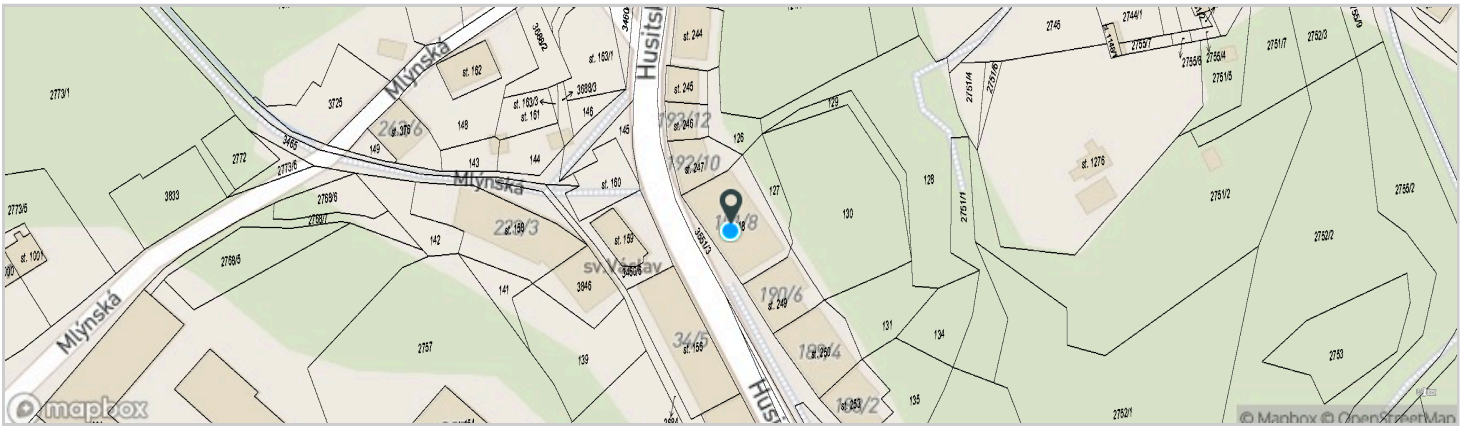

Fotodokumentace nemovitosti:



Copyright © (2014-2025), CenovaMapa, OctopusPro, s.r.o. - Všechna práva vyhrazena
Použití tohoto reportu se řídí VOP OctopusPro, s.r.o. (www.octopuspro.cz).

TRŽNÍ CENA NEMOVITOSTI

5 522 856 Kč

30 513 Kč/m²

Tržní cena domu je vypočtena průměrováním vybraných reálných kupních cen (Kč/m2) z listin katastru nemovitostí u podobných domů, z nejbližšího okolí analyzovaného místa. Celková cena je vypočtena na základě zadání parametrů nemovitosti: podlahová plocha, počet podlaží, počet bytových jednotek, stav, konstrukce budovy a další.

Zdroj dat:	**Katastr nemovitostí**
Stáří dat:	**6 měsíců**

Statistické parametry:

Průměr:	**30 513**	Kč/m²
Medián:	**39 451**	Kč/m²
Konečná cena (průměr)	**5 522 856**	Kč
Minimum:	**10 788**	Kč/m²
Maximum:	**41 091**	Kč/m²
Směrodatná odchylka:	**14 096.0**	Kč/m²
Počet měření:	**5**	

S 95% pravděpodobností leží odhadovaná cena v intervalu: **18 157** - **42 869** Kč/m²

Počet okolních nemovitostí pro srovnání: **10**

Seznam kupních cen staveb v poptávané lokalitě (adresní místo stavby), ze kterých je určena průměrná tržní cena:

Kupní cena (Kč/m²)	Plocha podlah. (m²)	Plocha st.par. (m²)	Plocha pozemek (m²)	Adresa	Stáří stavby	Počet podlaží	Konstr. stavby	Řízení (kup. listina)	Datum transakce	Vzdálenost (m)
41 091	270-280 [1]	142		Sídliště 553 Krupka	1960	3	Cihla	V-348/2025-509	1.2025	540
40 960	270-280 [1]	139		Sídliště 552 Krupka	1960	3	Cihla	V-348/2025-509	1.2025	550
39 451	125-130	107	717	Na Výrovce 647 Krupka	2008	2	Cihla	V-7018/2024-509	12.2024	690
20 276	95-100 [1]	75	150	Bohosudovská 325/34 Krupka	1945	2	Cihla	V-6708/2024-509	12.2024	400
10 788	210-220 [1]	165		Poštovní 452/1 Krupka	1945	2	Cihla	V-7000/2024-509	12.2024	420

[1] podlahová plocha je vypočtena nepřímo, z jiných parametrů a může se významně odlišovat od skutečné hodnoty.

Seznam nabídkových cen staveb v nejbližším okolí poptávané lokality.

(až 20 podobných staveb v nejbližším okolí)

Plocha podlah. (m²)	Cena (Kč/m²)	Cena aktuální (Kč)	Cena počáteční (Kč)	Adresa	Zahájení inzerce	Nabídka dnů	Aktivní inzerce	Počet jednotek	Počet podlaží	Konstr. stavby	Vzdálenost (m)
97	95 876	9 300 000	9 300 000	Slunečná 246 Vrchoslav, Krupka	10.10.2024	127	Ne	1	1	Dřevo	1 km
85	80 000	6 800 000	6 900 000	Alejní 678 Krupka	27.08.2024	75	Ne	1	1	Cihla	1 km
105	64 762	6 800 000	6 800 000	Alejní 678 Krupka	10.11.2024	30	Ne	1	1	Cihla	1 km
160	53 125	8 500 000	8 500 000	U Lanovky 805 Bohosudov, Krupka	18.02.2025	1	Ne	1	1	Cihla	1 km
164	51 829	8 500 000	8 500 000	U Lanovky 805 Bohosudov, Krupka	21.02.2025	7	Ne	1	1	Cihla	1 km
147	36 054	5 300 000	5 300 000	Libušín 139/3 Krupka	28.02.2025	48	Ano	1	1	Cihla	150
281	33 060	9 290 000	9 863 000	Dlouhá 644 Bohosudov, Krupka	12.09.2024	105	Ne	1	1	Cihla	1 km
144	31 944	4 600 000	4 600 000	Cínová 131 Krupka	30.10.2024	-	Ano	1	1	Cihla	130
155	30 484	4 725 000	5 250 000	Žižkova 68/2 Bohosudov, Krupka	05.10.2024	-	Ano	2	1	Cihla	900

Copyright © (2014-2025), CenovaMapa, OctopusPro, s.r.o. - Všechna práva vyhrazena
Použití tohoto reportu se řídí VOP OctopusPro, s.r.o. (www.octopuspro.cz).

204	20 588	4 200 000	4 200 000	Mlýnská 263/6 Krupka	07.01.2025	100	Ano	3	3	Cihla	78
387	18 062	6 990 000	6 990 000	K Plovárně 467/6 Bohosudov, Krupka	29.01.2025	78	Ano	1	1	Cihla	850
431	12 761	5 500 000	5 990 000	Bohosudovská 97/6 Bohosudov, Krupka	16.12.2024	122	Ano	1	3	Cihla	860
253	11 067	2 800 000	2 800 000	Libušín 246/1 Krupka	05.12.2024	133	Ano	1	1	Cihla	140
488	7 377	3 600 000	4 000 000	Poštovní 452/1 Krupka	05.06.2024	-	Ne	1	2	Cihla	410

Základní informace o nemovitosti

INFORMACE O PARCELE:

Nahlížení (KN):	ZOBRAZIT
LV:	1511
Typ parcely:	**Stavební**
Druh pozemku:	**Zastavěná plocha a nádvoří**
Číslo parcely:	**st. 248**
Katastrální území:	**Krupka (675261)**
Výměra parcely:	**367 m^2**

OBECNÉ INFORMACE:

Adresní místo

Husitská 191/8
Krupka

Stavba ID:	**18419631**
Adres. místo ID:	**18559018**
Část obce:	**Krupka (409332)**
Obec:	**Krupka (567639)**
Okres:	**Teplice**
Kraj:	**Ústecký kraj**
Parcela ID:	**1068565509**
Stavba ID:	**18419631**
Katastr. území ID:	**Krupka (675261)**
Lat:	**50.683451**
Lon:	**13.857403**

Copyright © (2014-2025), CenovaMapa, OctopusPro, s.r.o. - Všechna práva vyhrazena
Použití tohoto reportu se řídí VOP OctopusPro, s.r.o. (www.octopuspro.cz).

Porovnání tržní ceny (Kč/m²) nemovitosti ve vybraných oblastech

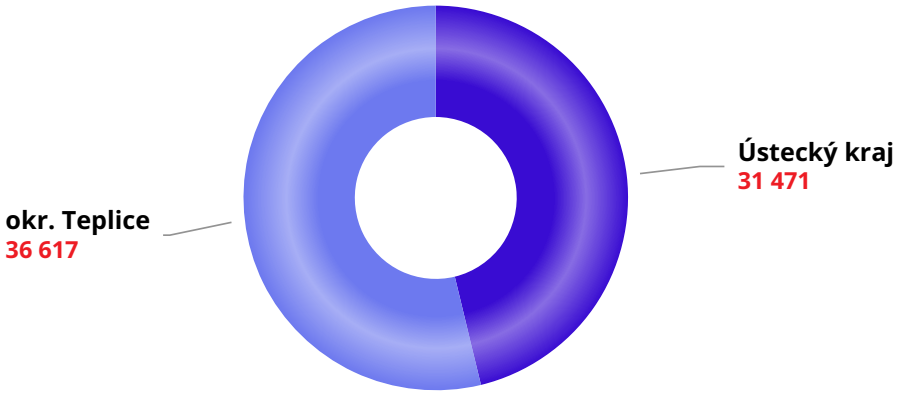

© 2025, OctopusPro

Pozn.: V grafu jsou zahrnuty pouze takové bytové jednotky, které mají parametry shodné nebo velmi blízké s dotazovanou nemovitostí.

Copyright © (2014-2025), CenovaMapa, OctopusPro, s.r.o. - Všechna práva vyhrazena
Použití tohoto reportu se řídí VOP OctopusPro, s.r.o. (www.octopuspro.cz).

Kriminalita v oblasti

Posuzovaná oblast: Část katast. území
(šedomodře označená ve středu mapy)

Bezpečnost v oblasti:

Zcela bezpečná oblast

0 trestných činů / km²

ve vybrané oblasti 0 deliktů

Index kriminality:

Nejbližší okolí: kružnice (R=5 km)	145
Nejbližší město:	87
Okres:	128
Kraj:	139
ČR:	122

Statistika krim. deliktů v oblasti (za posledních 12 měsíců):

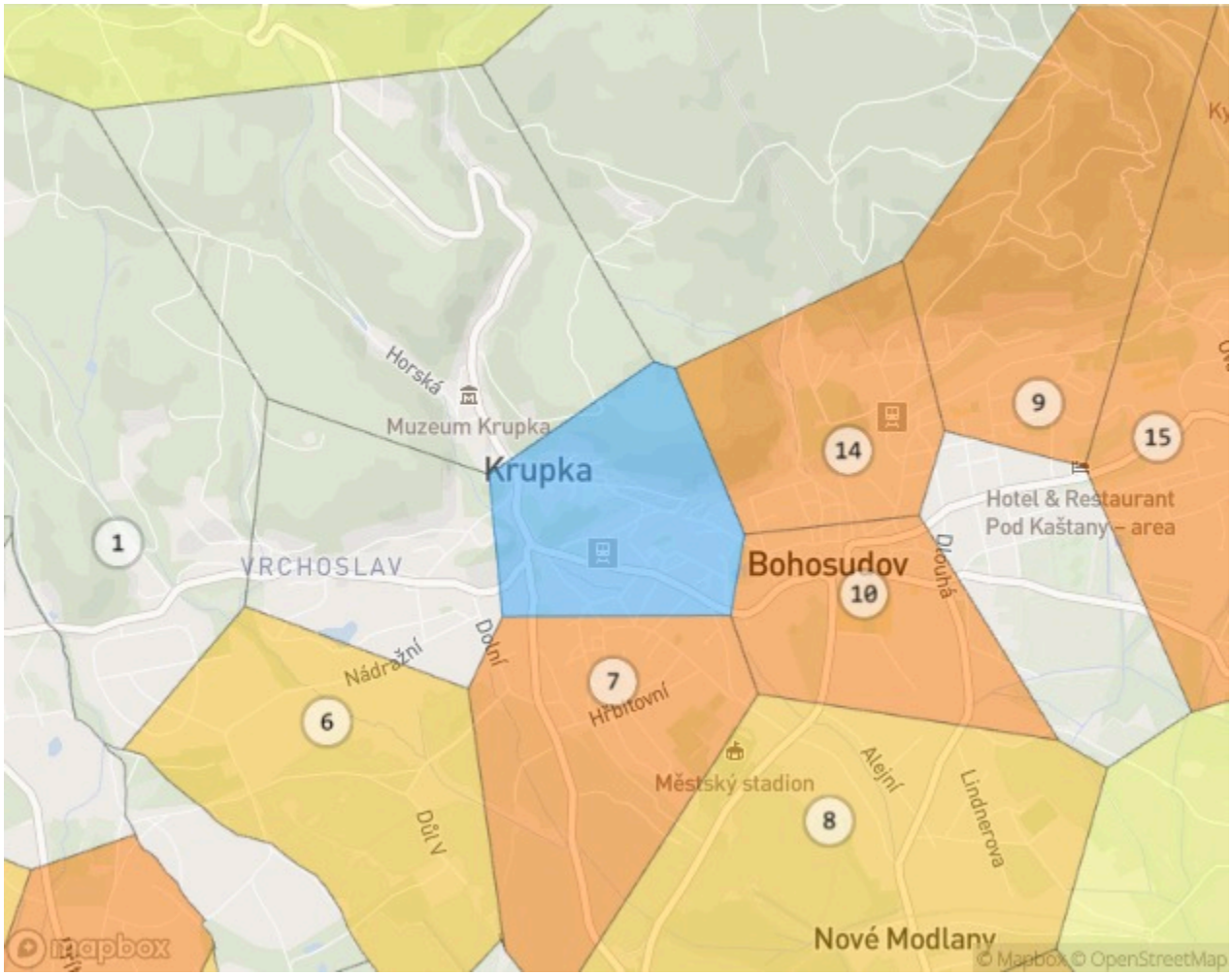

Index kriminality (Crime Index - CI) udává poměr počtu trestných činů ve vybrané oblasti (město, okres, kraj) na 10 000 obyvatel, za dobu 1 roku.

Copyright © (2014-2025), CenovaMapa, OctopusPro, s.r.o. - Všechna práva vyhrazena
Použití tohoto reportu se řídí VOP OctopusPro, s.r.o. (www.octopuspro.cz).

Záplavové oblasti

Posouzení záplavové oblasti:

100 - letá voda
malé riziko záplav
v této oblasti byly během posledních 100 let registrovány záplavy

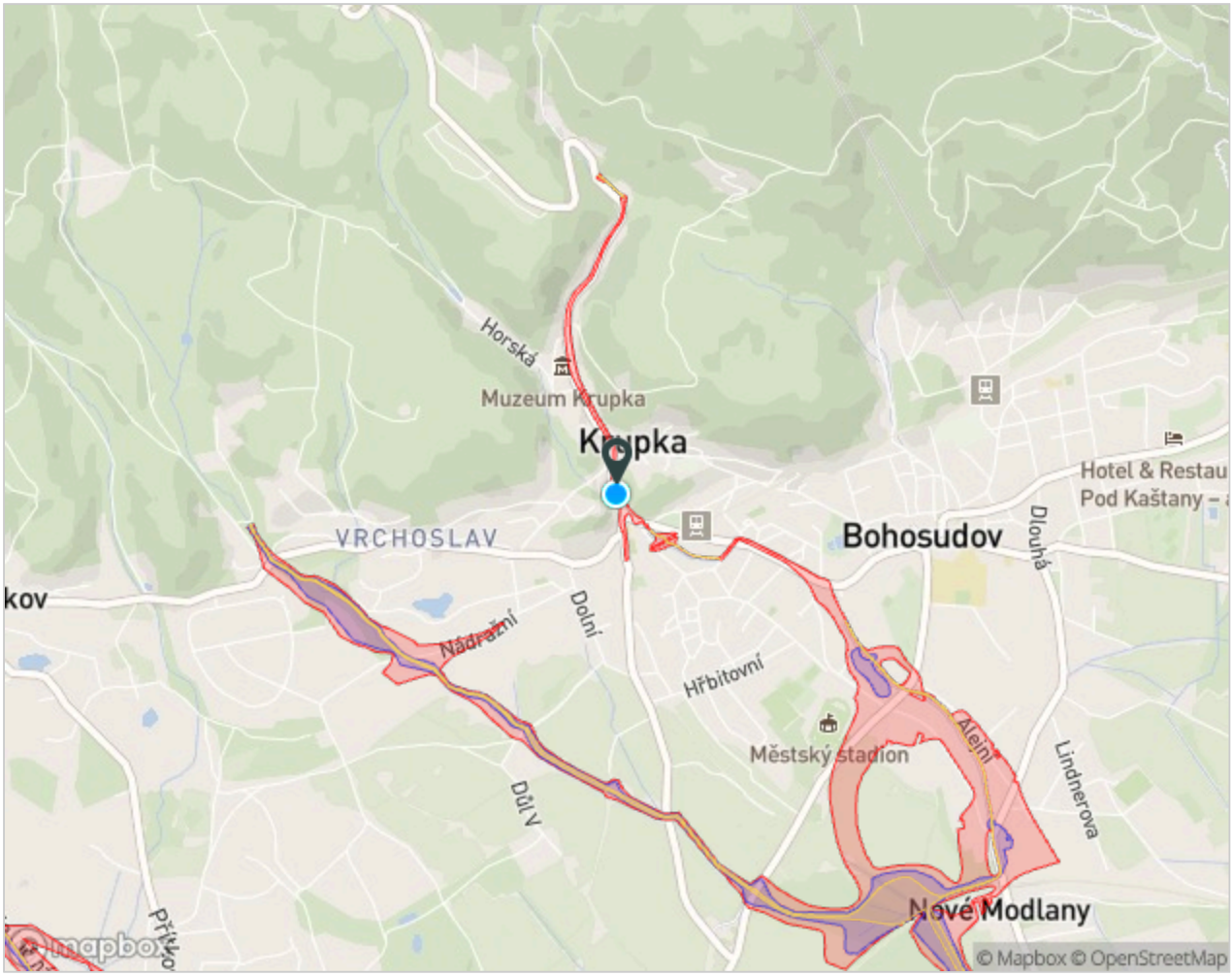

zdroj: dibavod.cz

100 letá voda 20 letá voda 5 letá voda

Copyright © (2014-2025), CenovaMapa, OctopusPro, s.r.o. - Všechna práva vyhrazena
Použití tohoto reportu se řídí VOP OctopusPro, s.r.o. (www.octopuspro.cz).

POSUDEK CENOVÉHO ODHADU VYPRACOVAL:

Šmídová Černá Anna

TELEFON:
+420 608 666 968

E-MAIL:
info@annacerna.cz

SPOLEČNOST:
Anna Černá Reality s.r.o.

Zdrojem použitých cenových údajů jsou listiny (kupní smlouvy) katastru nemovitostí. Výpočty odhadů tržních cen nemovitostí jsou zprostředkovány aplikací CenovaMapa.cz. Poskytovatel tohoto reportu nenese jakoukoliv odpovědnost za správnost a úplnost výstupů a neodpovídá za skutečnou škodu ani za ušlý zisk. Tento report nenahrazuje znalecký posudek.

Copyright © (2014-2025), CenovaMapa, OctopusPro, s.r.o. - Všechna práva vyhrazena
Použití tohoto reportu se řídí VOP OctopusPro, s.r.o. (www.octopuspro.cz).